SBB CFF FFS

BAT

ÖV Information 2.0 auf Basis von offenen Daten - wie macht die SBB da mit?

Christian Trachsel, 19. Juni 2015

Als Open Data werden jene Daten verstanden, welche die SBB in **maschinenlesbarer** Form und **kostenfrei** öffentlich zur **freien Sekundärnutzung** zur Verfügung stellen.

Ziel

- Sie kennen die Position der SBB für die Weitergabe von Daten an Dritte.
- Sie kennen den Prozess, wie sie bei der SBB Daten anfragen können.

Survey

http://svy.mk/1ReBJhm

Warum denkt die SBB über die Weitergabe von Daten nach

Weil wir müssen - Wieso wollen wir nicht



Das Bundesamt für Verkehr hat nämlich alle Transportunternehmen und Verbünde fürs nächste Jahr verpflichtet, ihre Daten lesbar in die Kundeninformationsplattform der SBB einzuspeisen. Und die SBB haben den Auftrag erhalten, bis Ende 2016 eine Open-Data-Schnittstelle aufzubauen. Da dürften einige nützliche Anwendungen auf uns zukommen.

Weil wir wollen - Wieso dürfen wir nicht

Evolution der Datenverwendung

Papierfahrplan

Evolution der Datenverwendung

Papierfahrplan

Digitalisierung



Evolution der Datenverwendung

Papierfahrplan | Digitalisierung | Interaktivität

Fahrplan - Auslegeordnung

Rohdaten | Rohdaten + Kalkulation | Rohdaten + Kalkulation ++

	Rohdaten / Bulk	Kalkuliert / Schnittstelle
SOLL	fahrplanfelder.ch gtfs.geops.ch	Solution Provider Fahrplan Transport.Opendata API
Prognose	CUS Open Data Plattform ÖV	Solution Provider Fahrplan Transport.Opendata API
Ist	InfoHub PT	

Beispiele auf Rohdaten (SOLL)

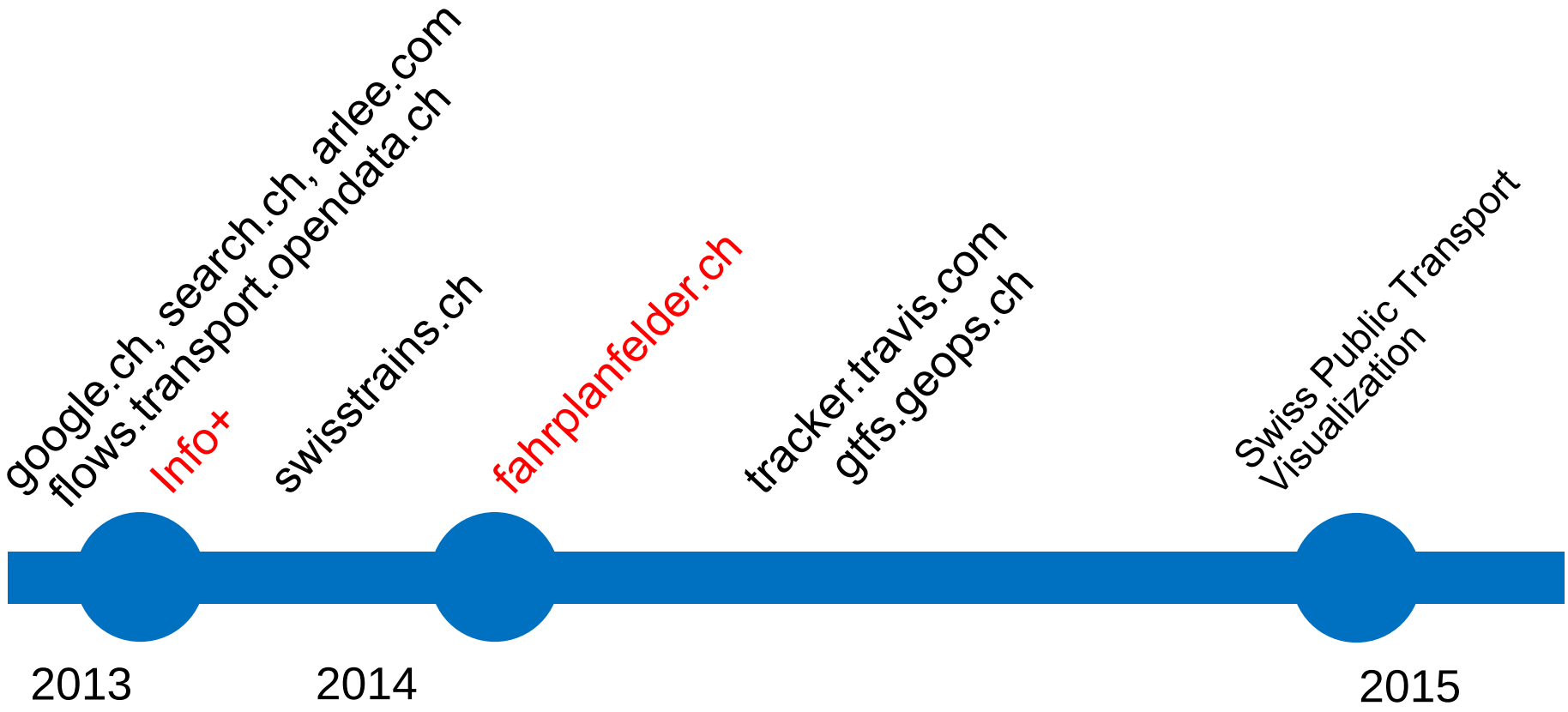

SBB CFF FFS

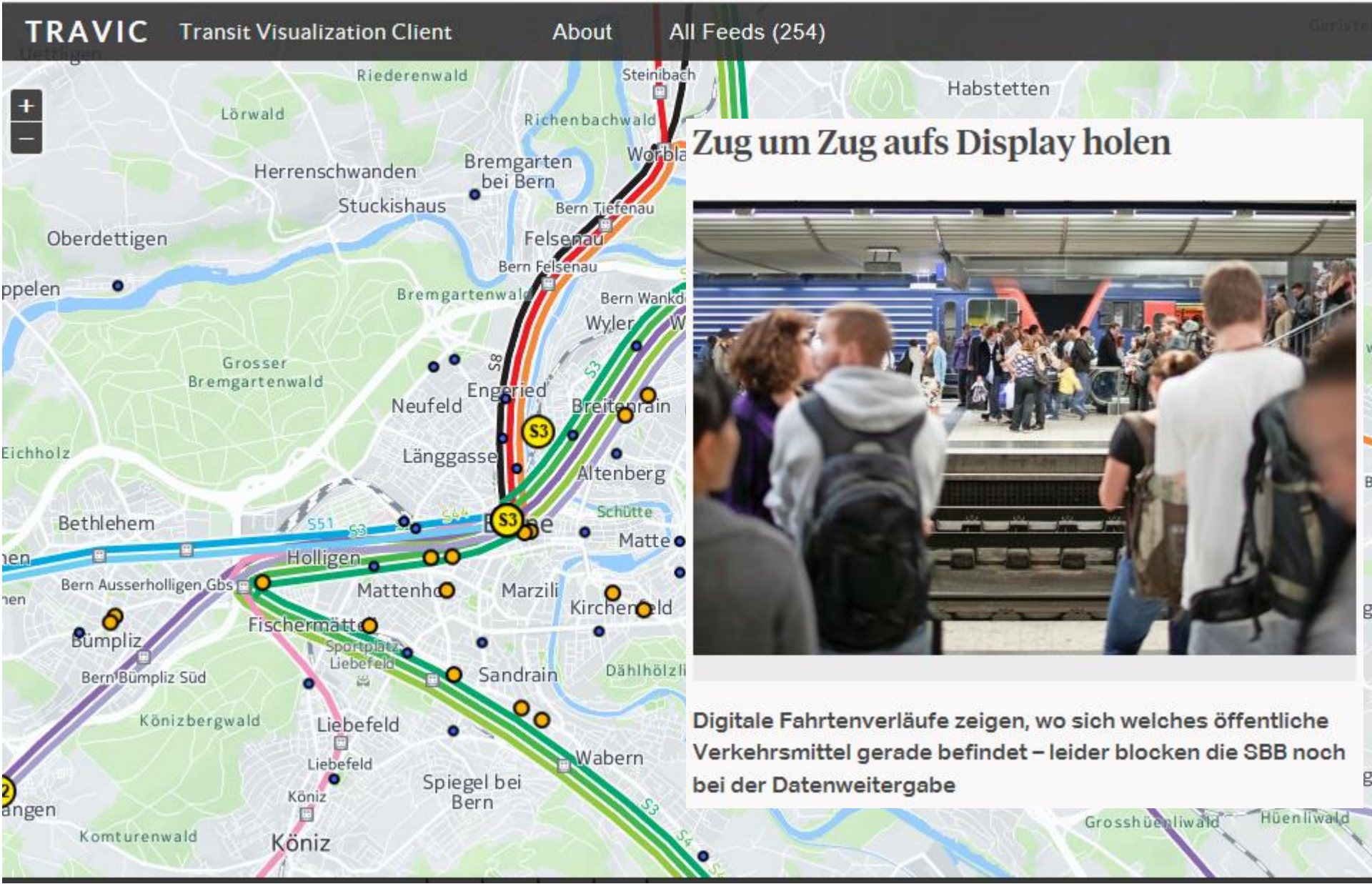

Zug um Zug aufs Display holen

Digitale Fahrtenverläufe zeigen, wo sich welches öffentliche Verkehrsmittel gerade befindet – leider blocken die SBB noch bei der Datenweitergabe

Swiss Public Transportation Visualization

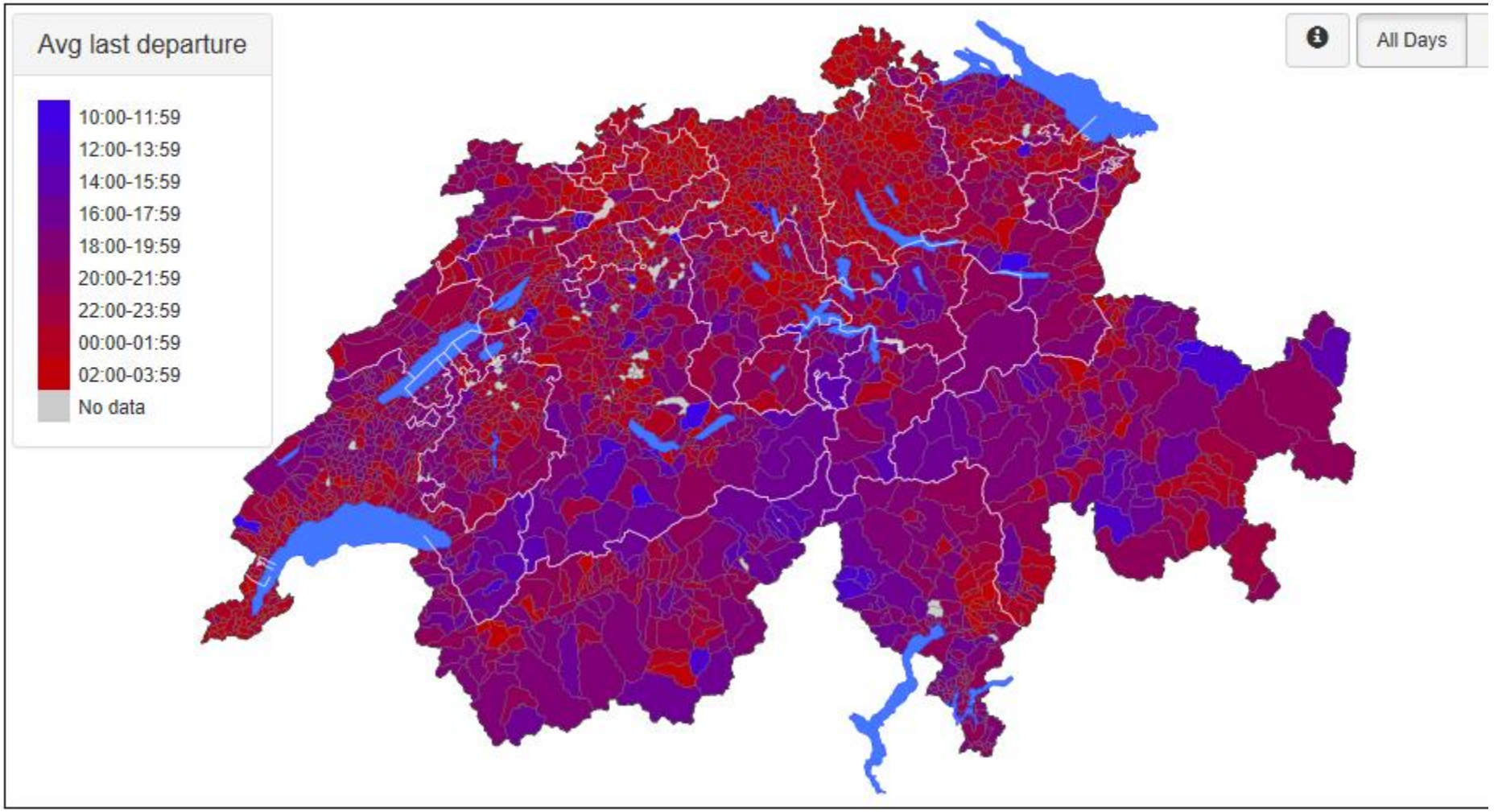

http://sptv.sam-e.ch/

Viadi

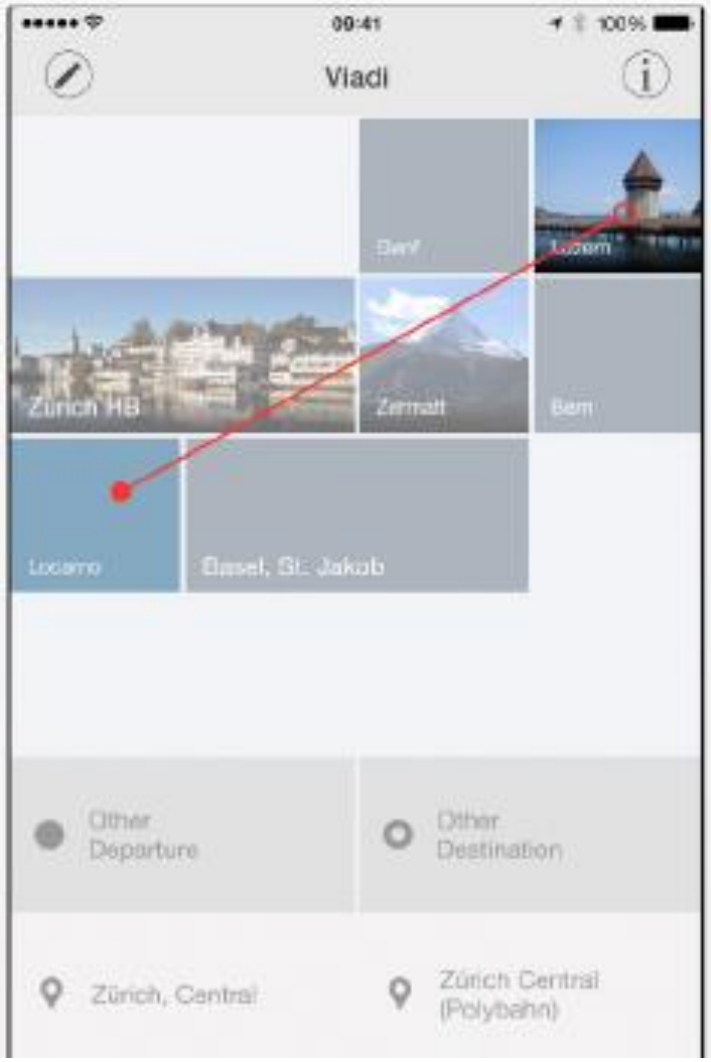
09:41
100%
Viadi
Bern
Luzern
Zürich HB
Zermatt
Bern
Locarno
Basel, St. Jakob
Other Departure
Other Destination
Zürich, Central
Zürich Central (Polybahn)

SAMSUNG
11:08
Viadi
Fiesch
Rösligtr.
Kronenstr.
Burgdorf
Central
Zürich
Anderer Startort
Anderer Zielort
Oberems
Fiescheralp
Zürich Central (Polybahn)
Zürich, Bahnhofquai/HB
GET IT ON
Google play

11:08
Viadi
Bahnhofplatz
ETHZ
Aarau
Central
Sonnenmattweg
Zürich, Zoo
Bernaplatz
Zürich HB
Anderer Startort
Anderer Zielort
Winterthur
Aarau, Aarepark
Zürich Central (Polybahn)
Zürich, Bahnhofquai/HB
Download on the
App Store

Beispiele auf kalkulierten Daten

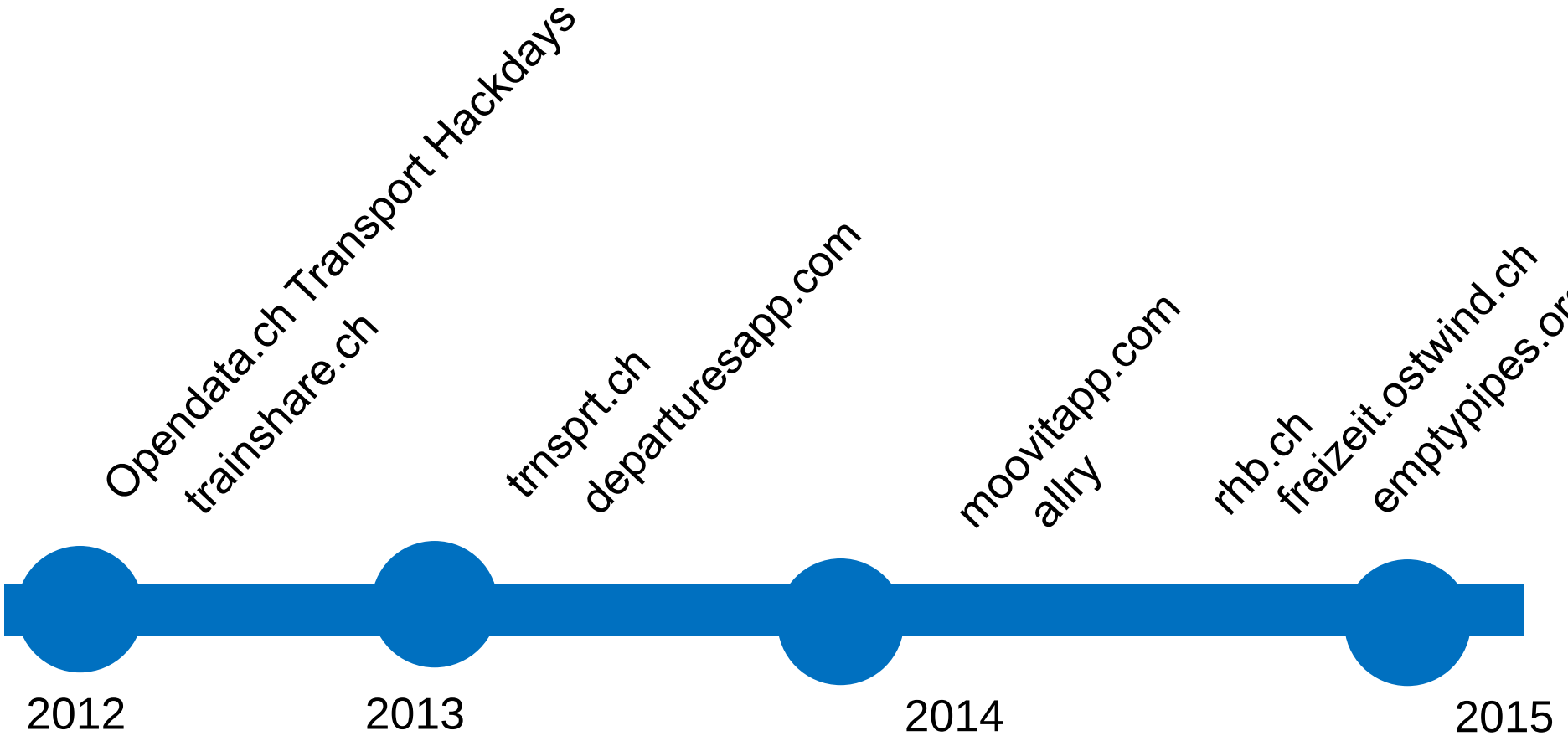

Reisezeit in Europa

Isochrone Maps of Europe

20 May 2015

Below is a map showing how long one would expect to travel to any point in Europe starting in Vienna, using only trains and walking at a brisk rate of 5 min / kilometer.

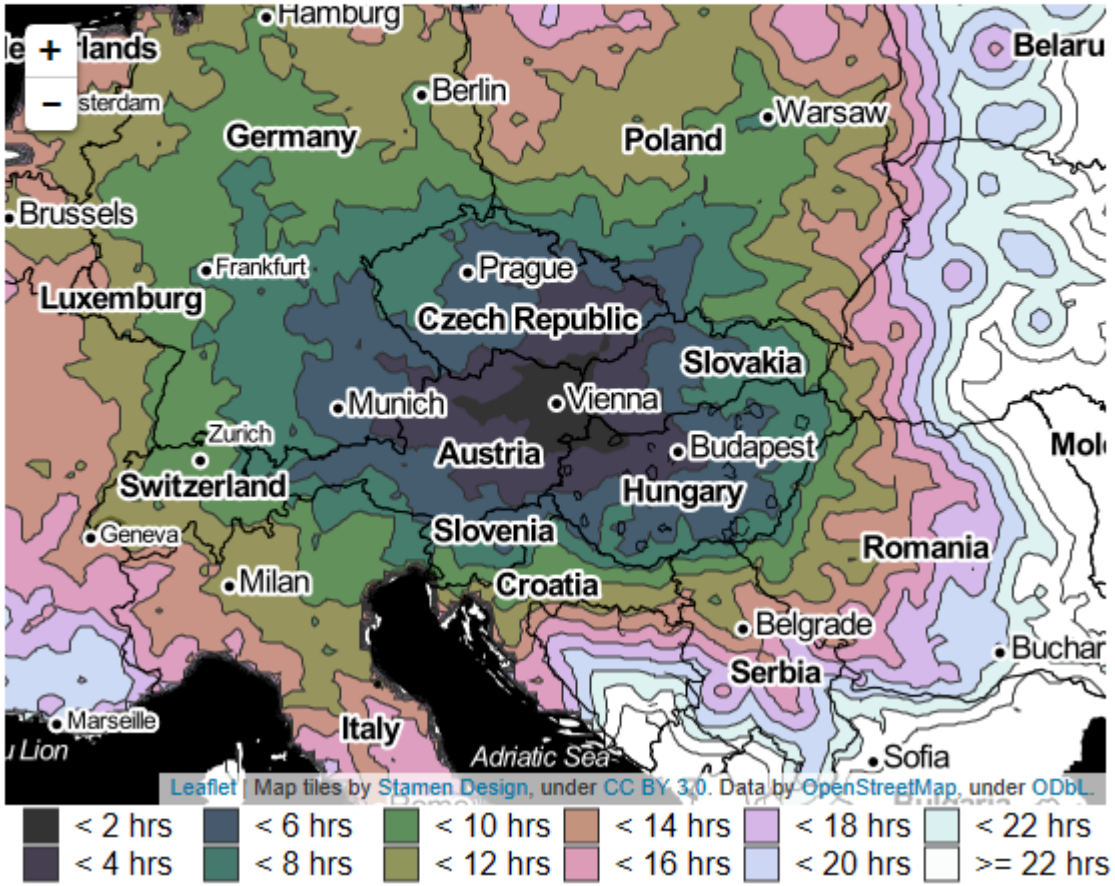

http://emptypipes.org/2015/05/20/europe-isochrone-map/

Ally

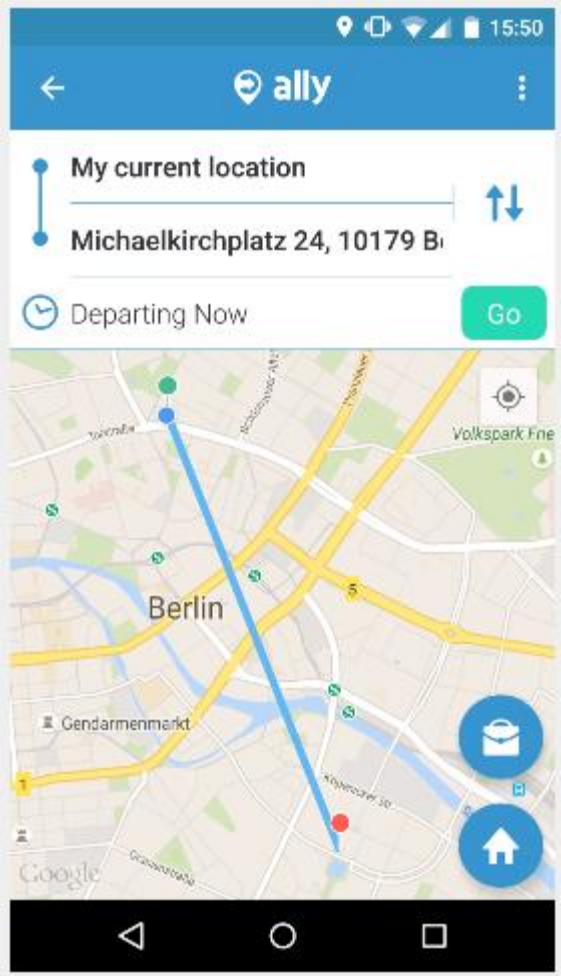
15:50
ally
My current location
Michaelkirchplatz 24, 10179 B
Departing Now
Go
Volkspark Fne
Berlin
Gendarmenmarkt
Google

15:50
ıia - Reisstraße 22, 13629 Berlin
Departing Now
41 mins 2,70 € 15:52 → 16:33
U8 S42 U7
53 mins 2,70 € 15:52 → 16:45
U8 U7
40 mins 2,70 € 15:57 → 16:37
U8 S42 U7
35 mins 8,12 € 15:49 → 16:24

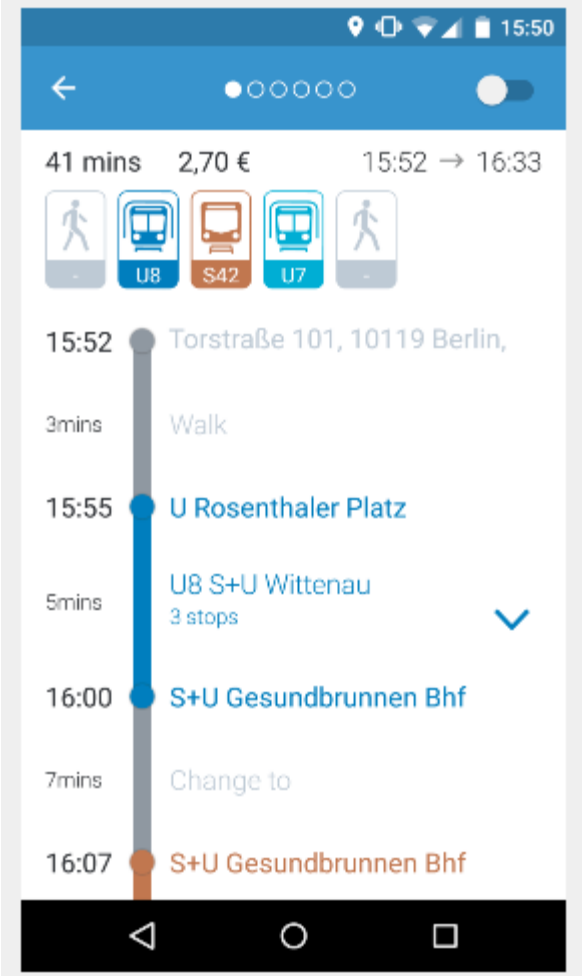
15:50
41 mins 2,70 € 15:52 → 16:33
U8 S42 U7
15:52 Torstraße 101, 10119 Berlin,
3mins Walk
15:55 U Rosenthaler Platz
5mins U8 S+U Wittenau
3 stops
16:00 S+U Gesundbrunnen Bhf
7mins Change to
16:07 S+U Gesundbrunnen Bhf

RHB

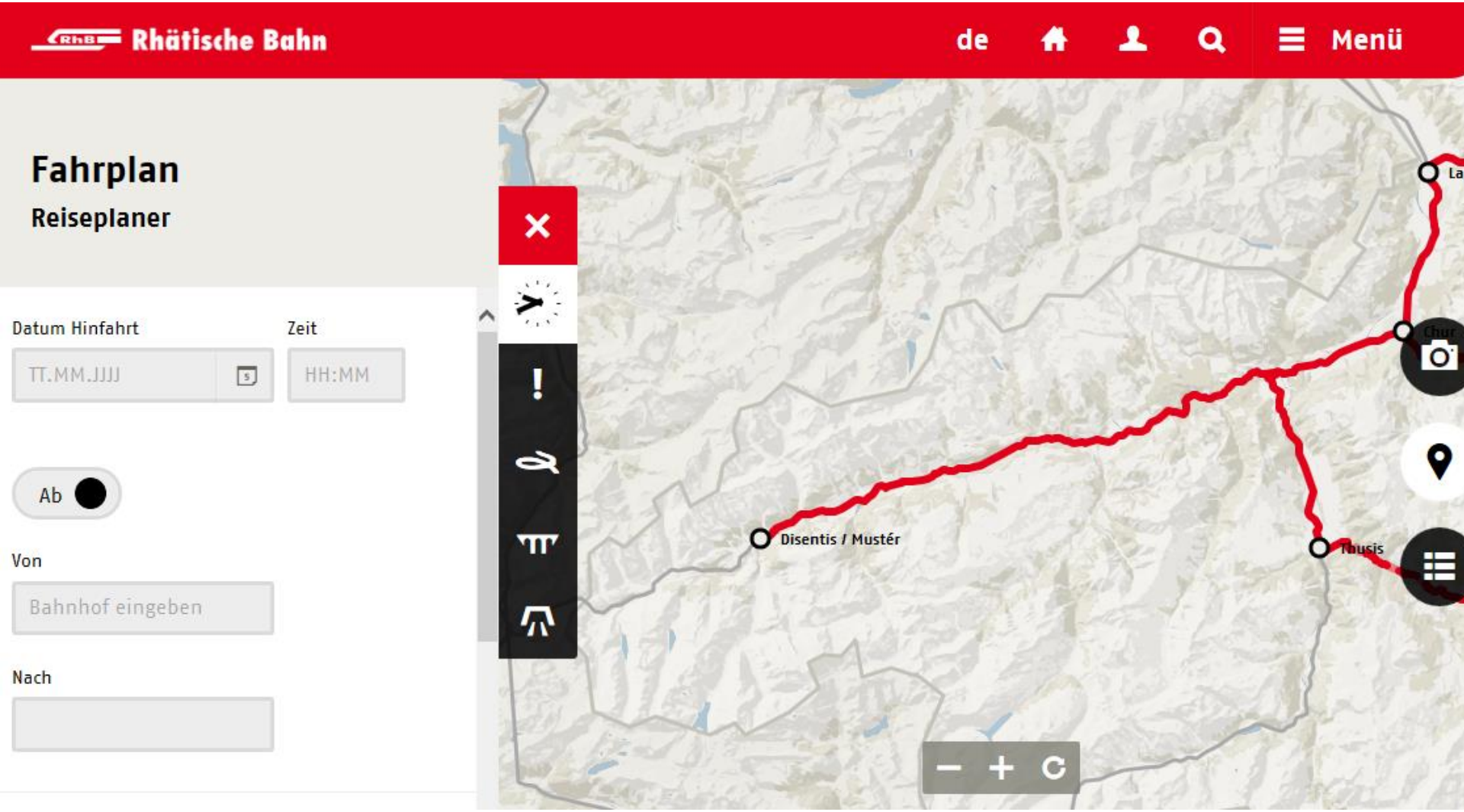
Rhätische Bahn
de
Menü
Fahrplan
Reiseplaner
Datum Hinfahrt
Zeit
TT.MM.JJJJ
HH:MM
Ab
Von
Bahnhof eingeben
Nach
Disentis / Mustér
Thusis

Bereitstellung von Reiseinformation an den Kunden

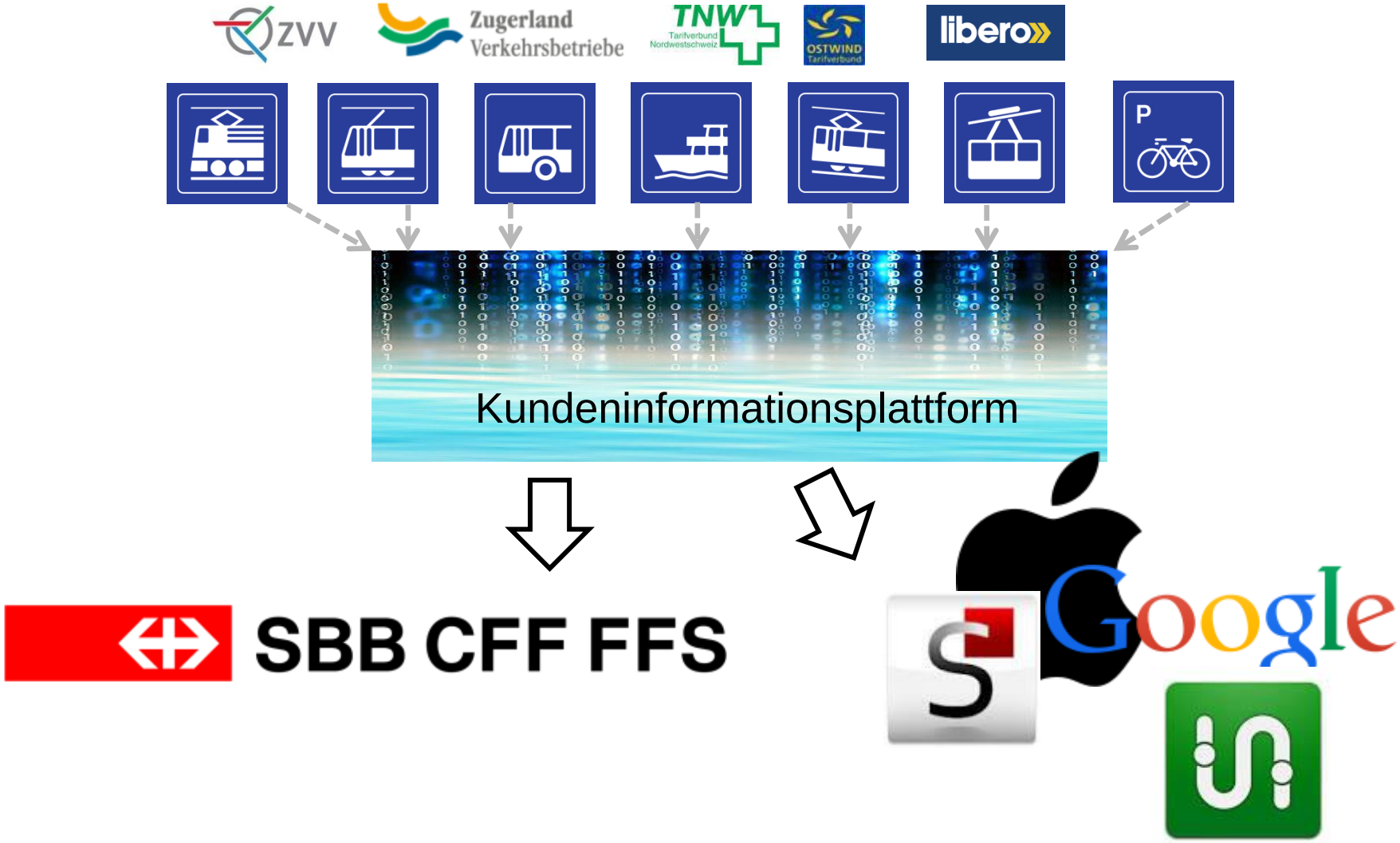

SBB CFF FFS

Prozessuales Vorgehen bei der SBB

Ein einfacher Prozess ermöglicht rasche Antwort auf Anfragen

Anfrager

Öffentliche Ansprechstelle
Kommunikation und Architektur

data@sbb.ch

Datenowner

Was braucht alles es dazu?

Technik

Recht

Die SBB stellt Daten Dritten ausschliesslich aufgrund vertraglicher Vereinbarungen zur Verfügung, sie kann ein angemessenes Entgelt verlangen.

Wieso Nutzungsbedingung?

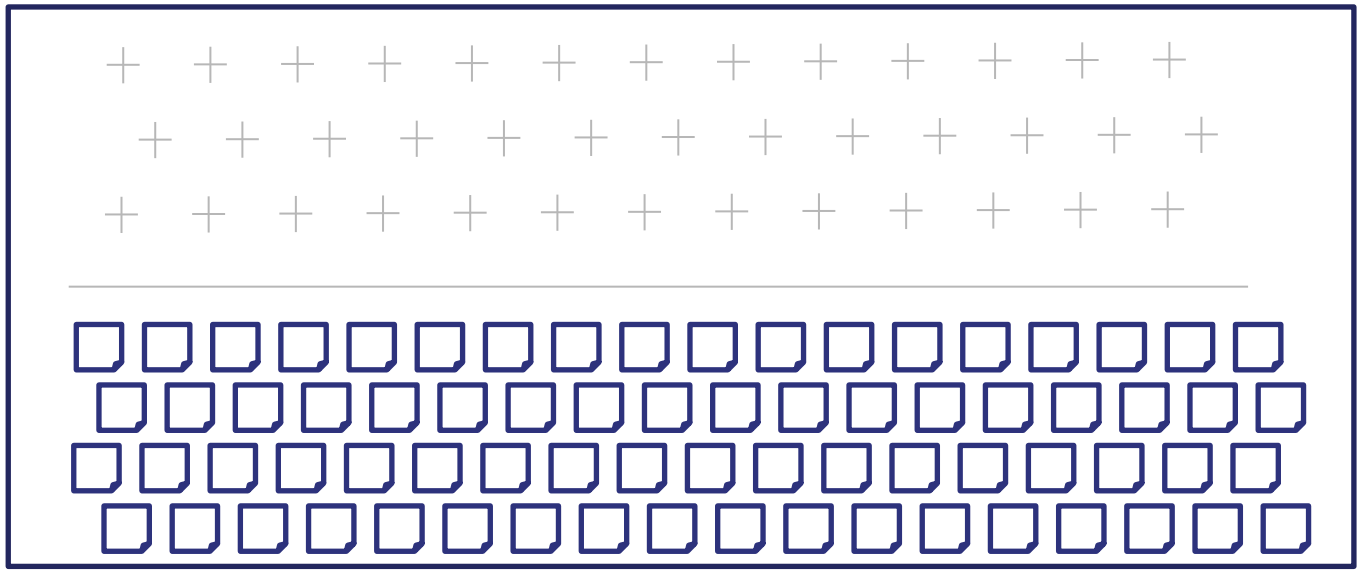

Mehrwert

Reine Daten

SBB CFF FFS

Packen wir es an.

christian.trachsel@sbb.ch
data@sbb.ch